# 智能亚当 APP

# 使用指南

V1.3

Android

iOS

# 目录

1. 登录注册 ..... 2

2. 首页 ..... 5

3. 警报通知 ..... 9

4. 查找设备 ..... 11

5. 活动日志 ..... 13

6. 一键导航 ..... 14

7. 电子栅栏 ..... 15

8. 历史轨迹 ..... 17

9. 设备详情 ..... 18

10. 个人中心 ..... 22

11. 修订文档 ..... 26

# 1.登录注册

## 1.1. 新用户注册

(1) 用户启动 APP 进入首页，系统出现用户尚未登录提示

(2) 点击【前往】出现登录注册页，新用户点击【创建新账户】跳转注册页

(3) 输入手机号/邮箱号

(4) 点击【发送验证码】，等待 60 秒后才可以再次发送

(5) 系统发送验证码至用户填写的手机号或邮箱号

(6) 输入 6 位验证码

(7) 输入 4 至 12 位密码

(8) 点击【注册】，成功则跳转回登录页；失败则出现错误原因

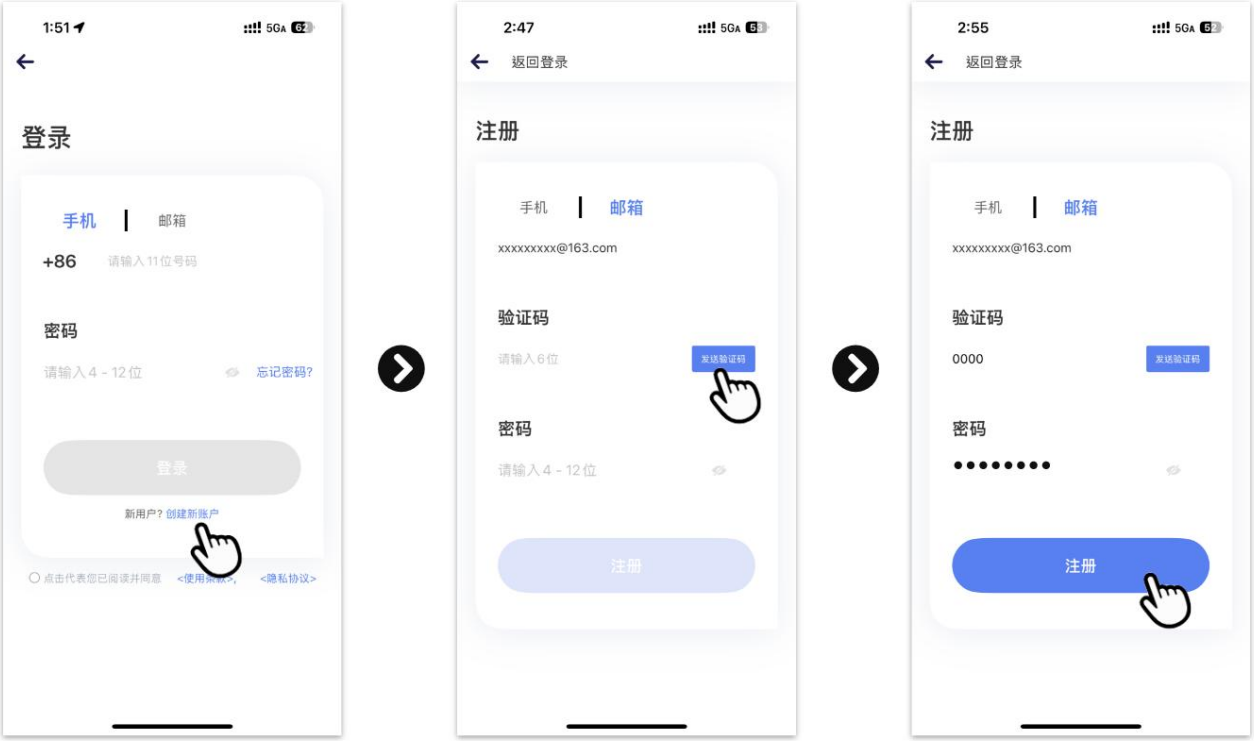

## 1.2. 用户登录

(1) 输入手机号/邮箱号

(2) 输入 4 至 12 位密码

(3) 勾选条款协议

(4) 点击【登录】，成功则跳转回首页；失败则出现错误原因

## 1.3. 密码重置

(1) 用户点击【忘记密码】跳转密码重置页

(2) 输入手机号/邮箱号

(3) 点击【发送验证码】，等待 60 秒后才可以再次发送

(4) 系统发送验证码至用户填写的手机号或邮箱号

(5) 输入 6 位验证码

(6) 输入 4 至 12 位新密码

(7) 点击【重置】，成功则跳转回登录页；失败则出现错误原因

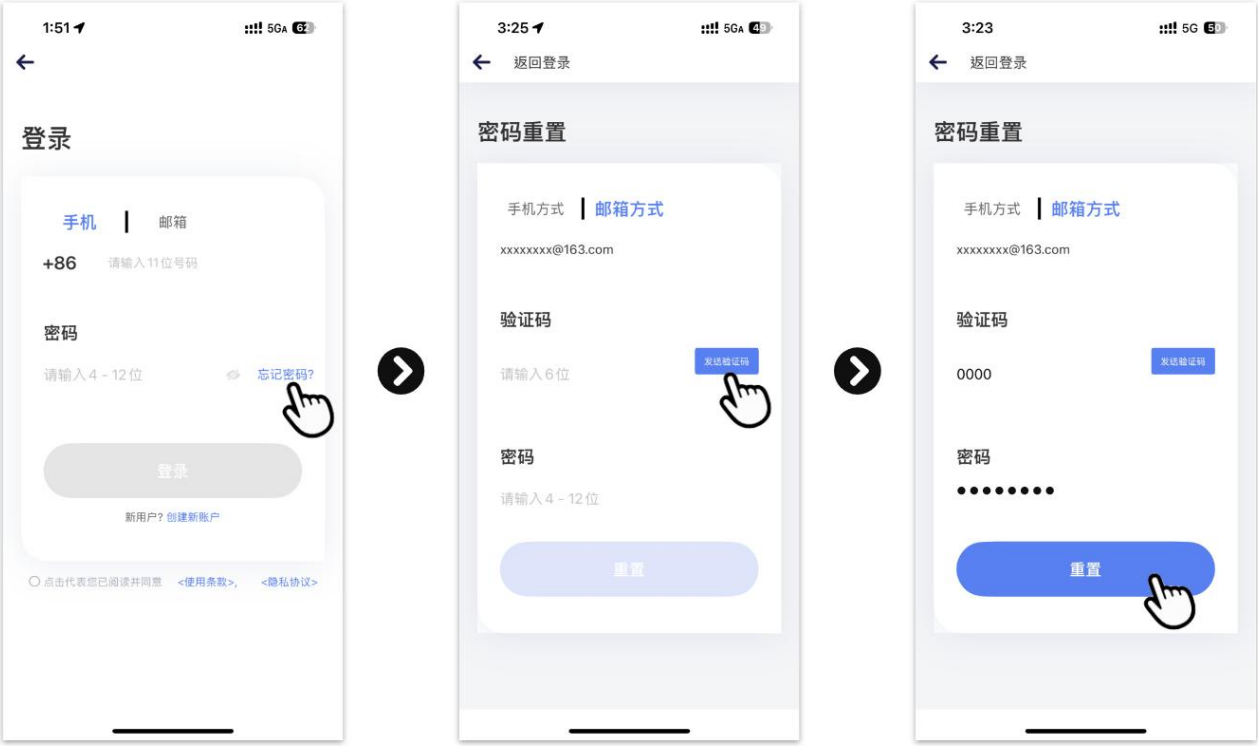

# 2.首页

## 2.1. 手机位置授权

(1) 当用户尚未开启手机位置授权，系统将弹出提示请求用户开启

(2) 点击【开启】跳转手机应用设置页

(3) 点击【位置】，选择 “仅在 APP 启用时使用位置”

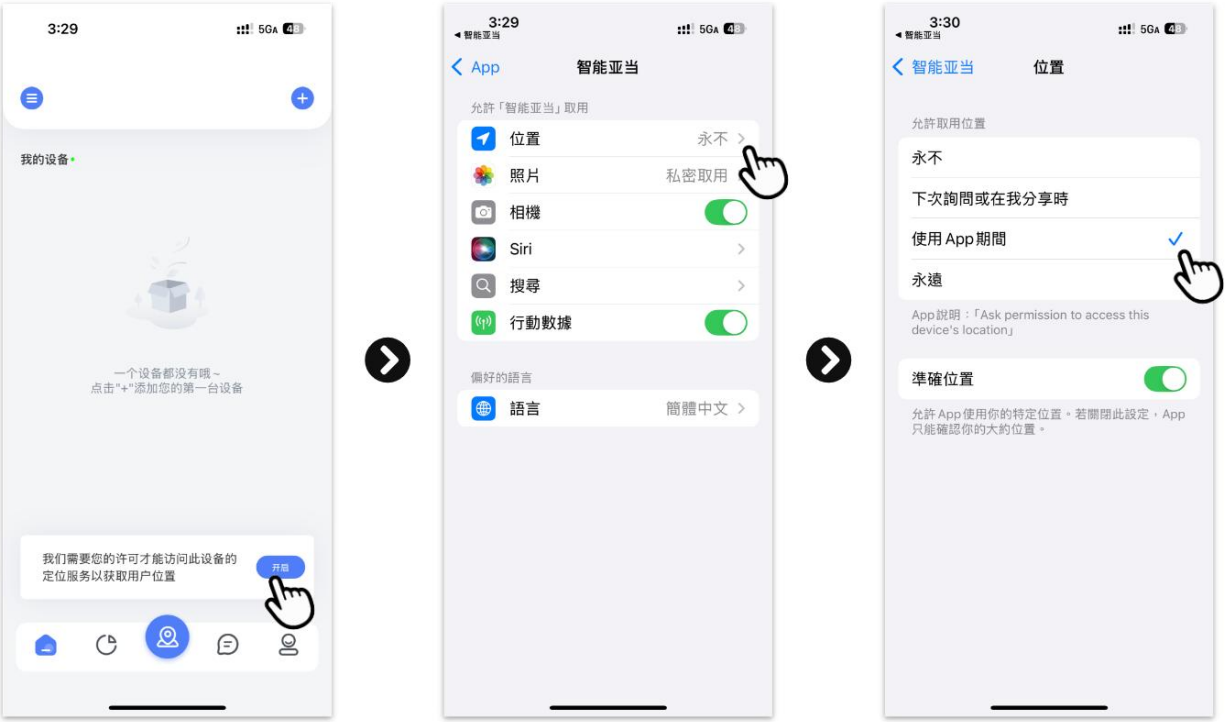

# 2.2. 添加设备

## 2.2.1.扫一扫

(1) 点击 “+” 出现添加方式弹窗，选择【扫一扫】

(2) 系统将请求用户开启手机相机

(3) 点击【前往】，跳转手机应用设置页

(4) 点击【相机】，选择 “开启”

(5) 将相机对准设备二维码进行扫描

(6) 等待系统确认设备信息

(7) 成功，即可位设备设置名称与头像；失败，则出现错误原因

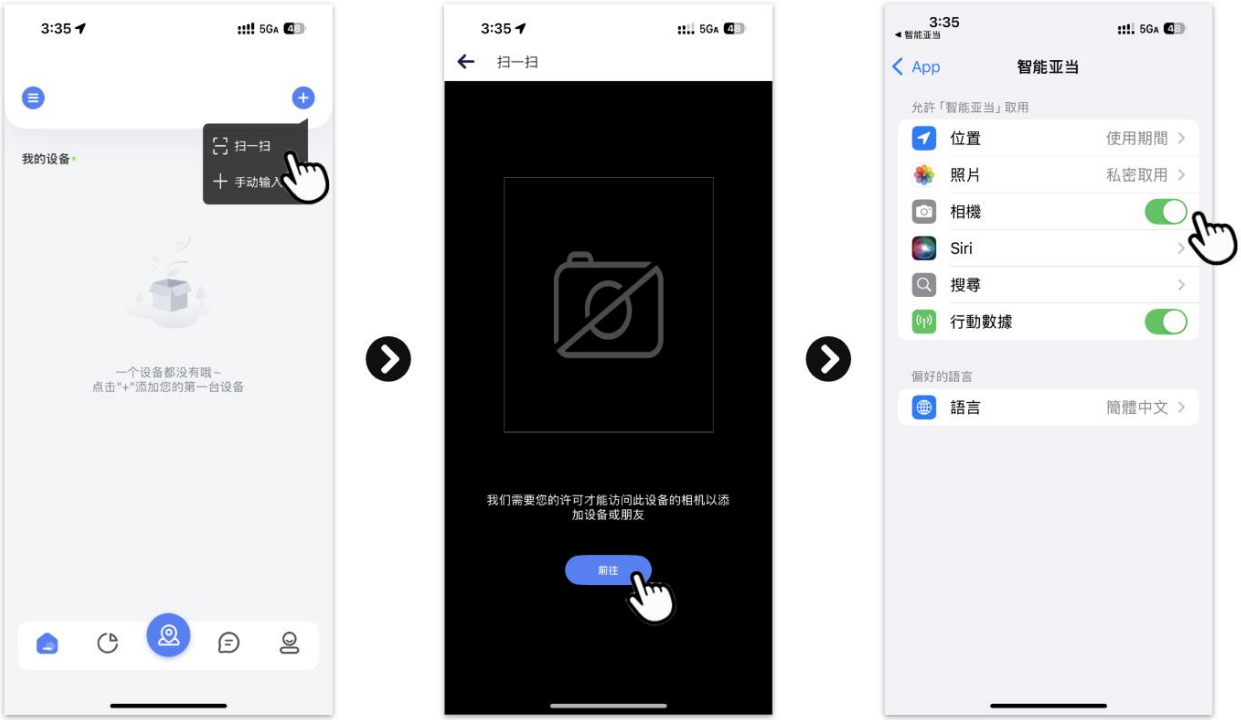

## 2.2.2.手动输入

(1) 点击 “+” 出现添加方式弹窗，选择【手动输入】

(2) 输入设备二维码下方 15 位 IMEI 序列号，点击【配对】

(3) 等待系统确认设备信息

(4) 成功，即可位设备设置名称与头像；失败，则出现错误原因

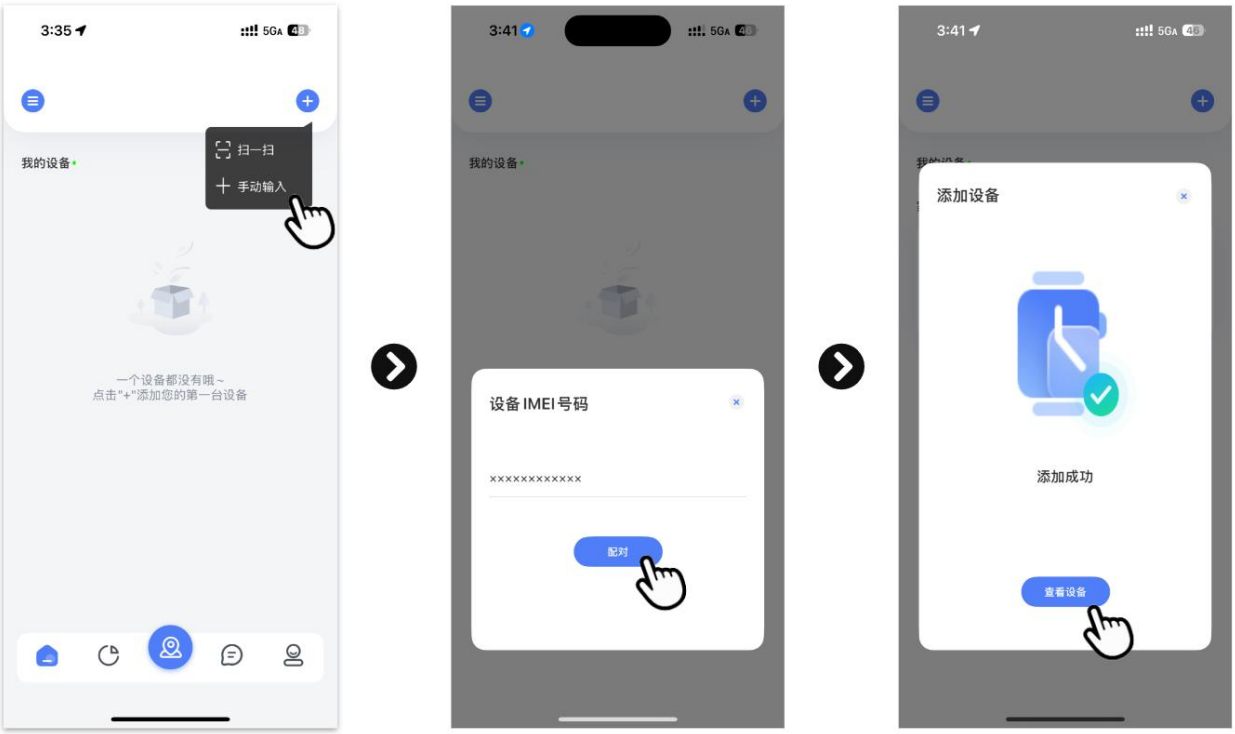

## 2.3. 设备状态

(1) 状态: 表示 WiFi 定位成功

(2) 状态: 表示 GPS 定位成功

(3) 状态: 表示 Beacon 定位成功

(4) 状态: 表示正在移动中

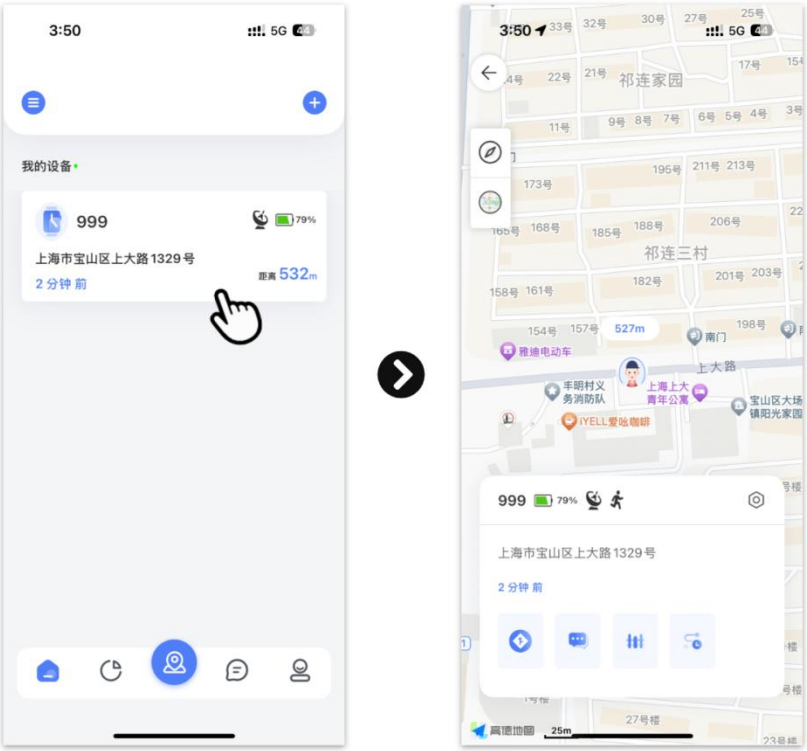

# 3.警报通知

## 3.1. 电量不足通知

(1) 当设备电量低于 20%，将向系统发出电量不足的消息

(2) 系统将检测用户是否在线并推送消息通知

(3) 用户在线，系统弹出电量不足通知;

(4) 用户离线，系统推送消息至用户手机或邮箱

## 3.2. 到达/离开栅栏通知

(1) 当系统检测设备到达/离开栅栏，将向用户发出警报通知

(2) 系统将检测用户是否在线并推送消息通知

(3) 用户在线，系统弹出电量不足通知;

(4) 用户离线，系统推送消息至用户手机或邮箱

# 4.查找设备

## 4.1. 用户定位切换

(1) 状态: 定位设备当前位置

(2) 状态: 定位用户当前位置

(3) 状态: 展示设备与用户两点位置

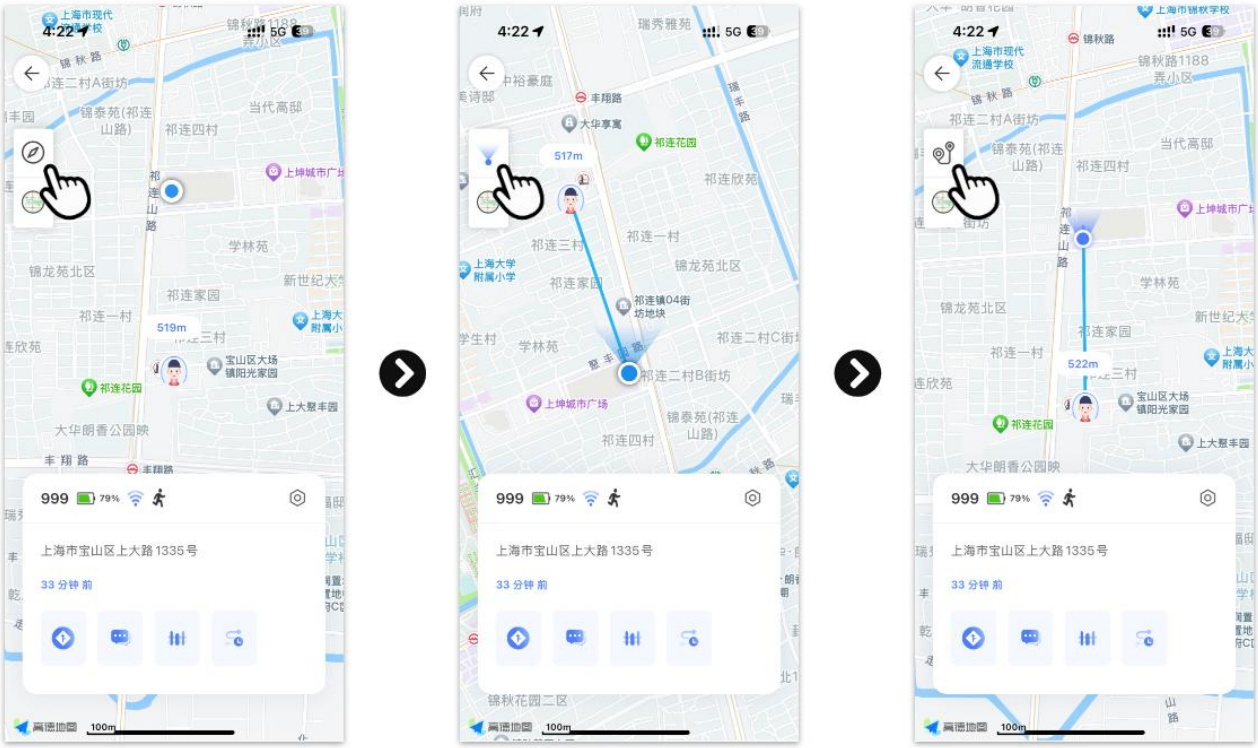

## 4.2. 地图切换

(1) 状态: 切换为普通地图模式

(2) 状态: 切换为卫星地图模式

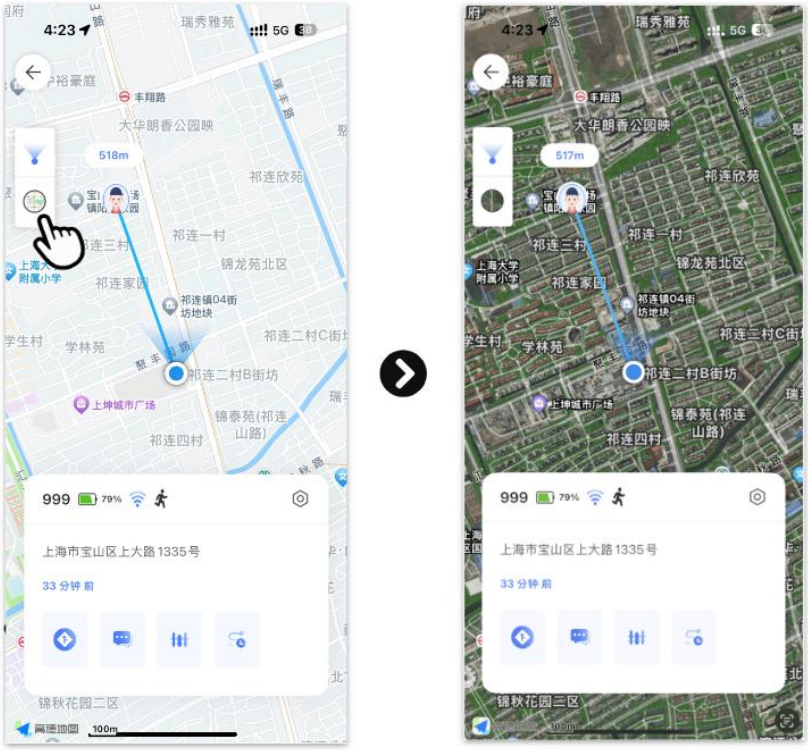

# 5.活动日志

(1) 点击 进入此设备的活动日志

(2) 查看此设备的活动纪录，如电量警报、到达/离开栅栏警报等

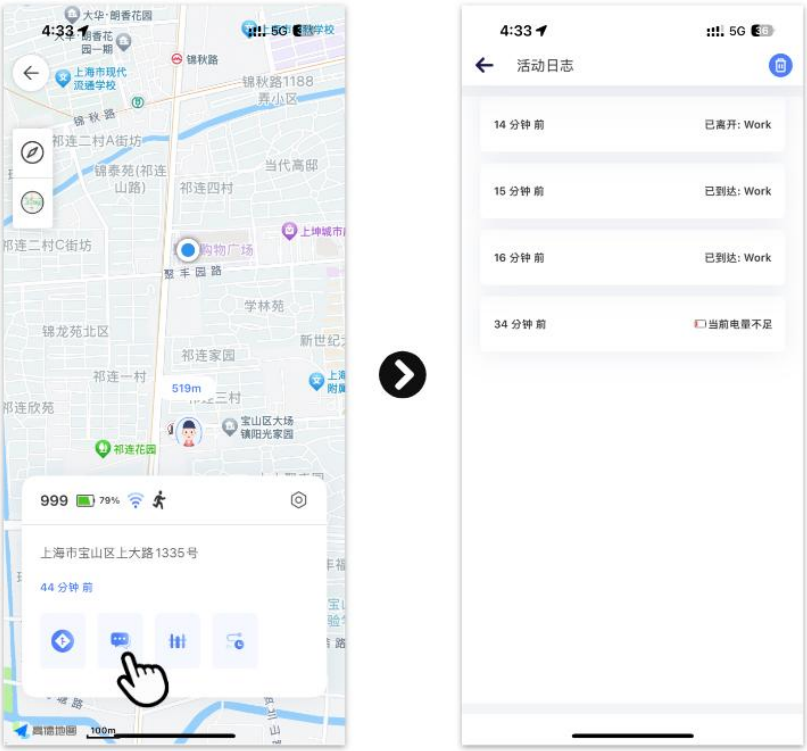

# 6.一键导航

(1) 用户在设备查找页，点击 出现导航选项

(2) 用户点击【第三方地图】，跳转并发起导航前往设备当前位置

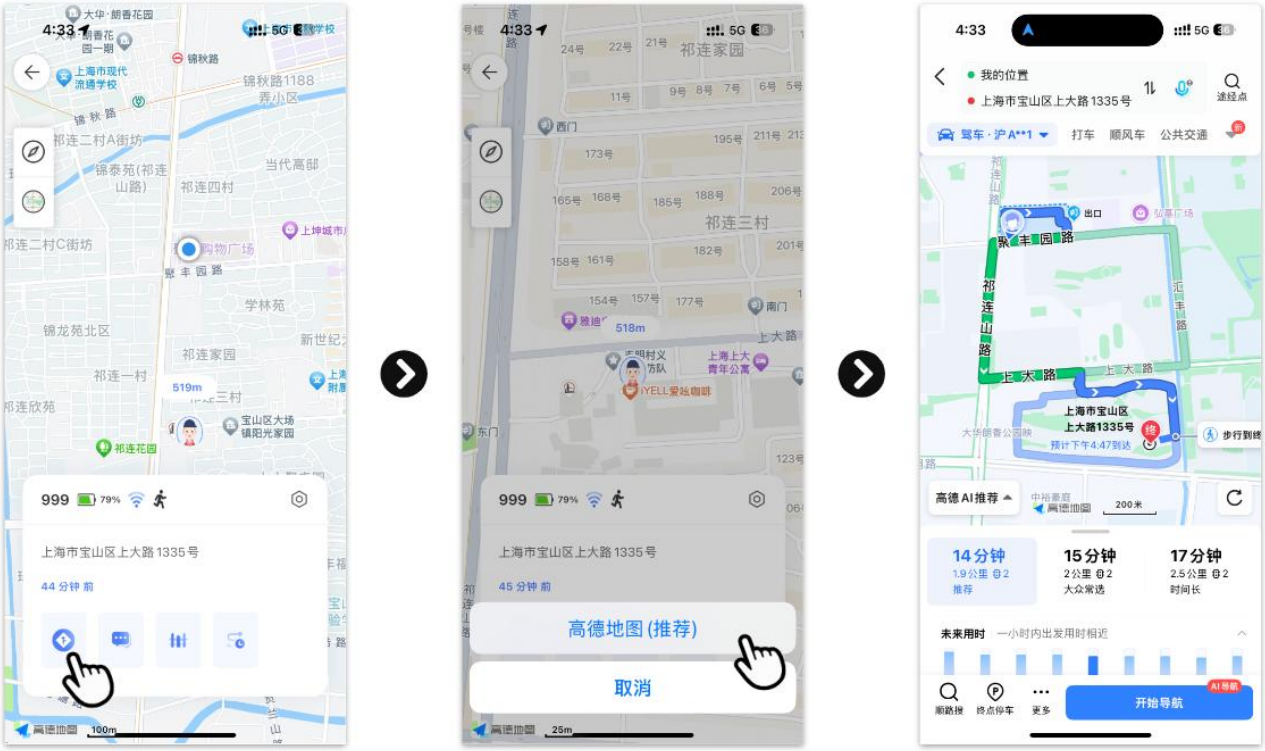

# 7.电子栅栏

## 7.1. 添加栅栏

(1) 用户在查找设备页，点击 进入此设备的电子栅栏页

(2) 点击“+”，进入栅栏地图页添加新的电子栅栏

(3) 系统将定位用户当前位置，并自动设置为栅栏位置(城市，地址)

(4) 输入栅栏名称，最多 8 位

(5) 可点击“+”/“-”缩放栅栏范围，最小 20 米，最大 2 公里

(6) 点击【添加】，跳转返回栅栏列表

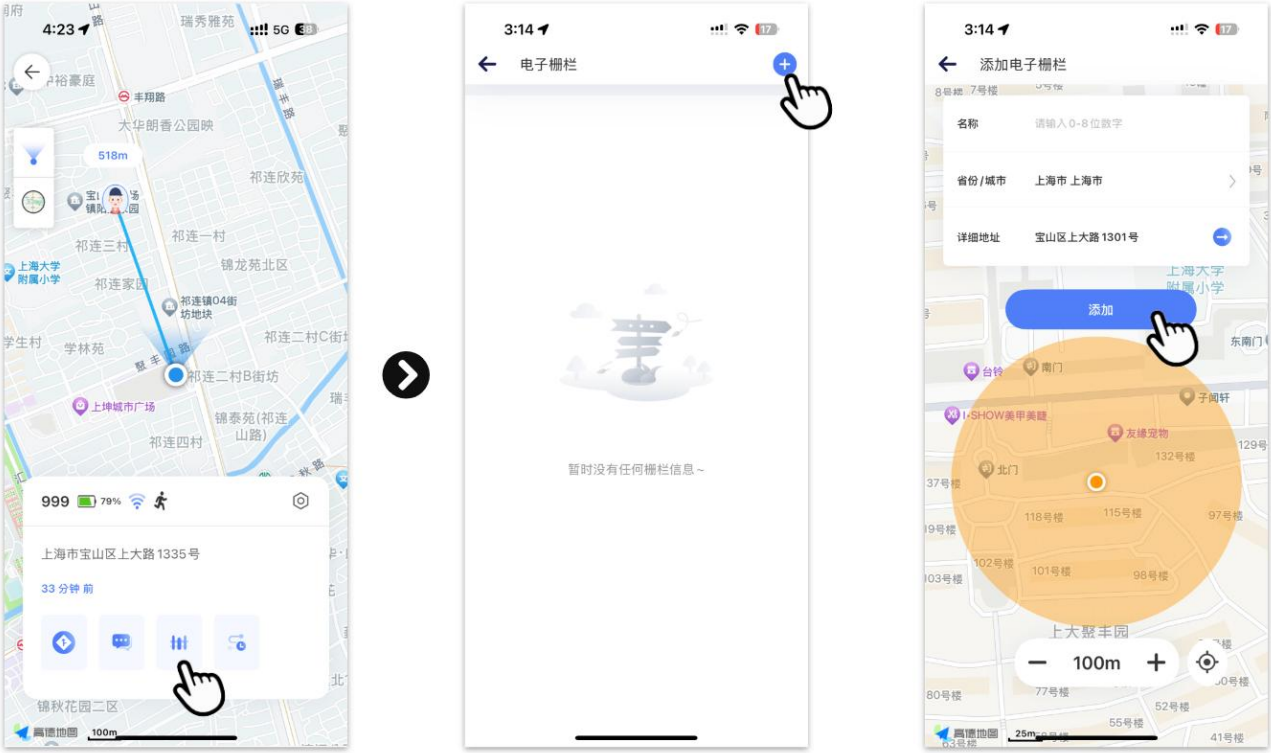

## 7.2. 编辑栅栏

(1) 用户点击已建栅栏，跳转至栅栏编辑页

(2) 用户可以点击 ，重新设置栅栏位置(城市/地址)；

(3) 用户可以手动输入地址，点击 定位该位置

(4) 输入栅栏名称，最多 8 位

(5) 左右滑动缩放栅栏范围，最小 20 米，最大 2 公里

(6) 点击【修改】，跳转返回栅栏列

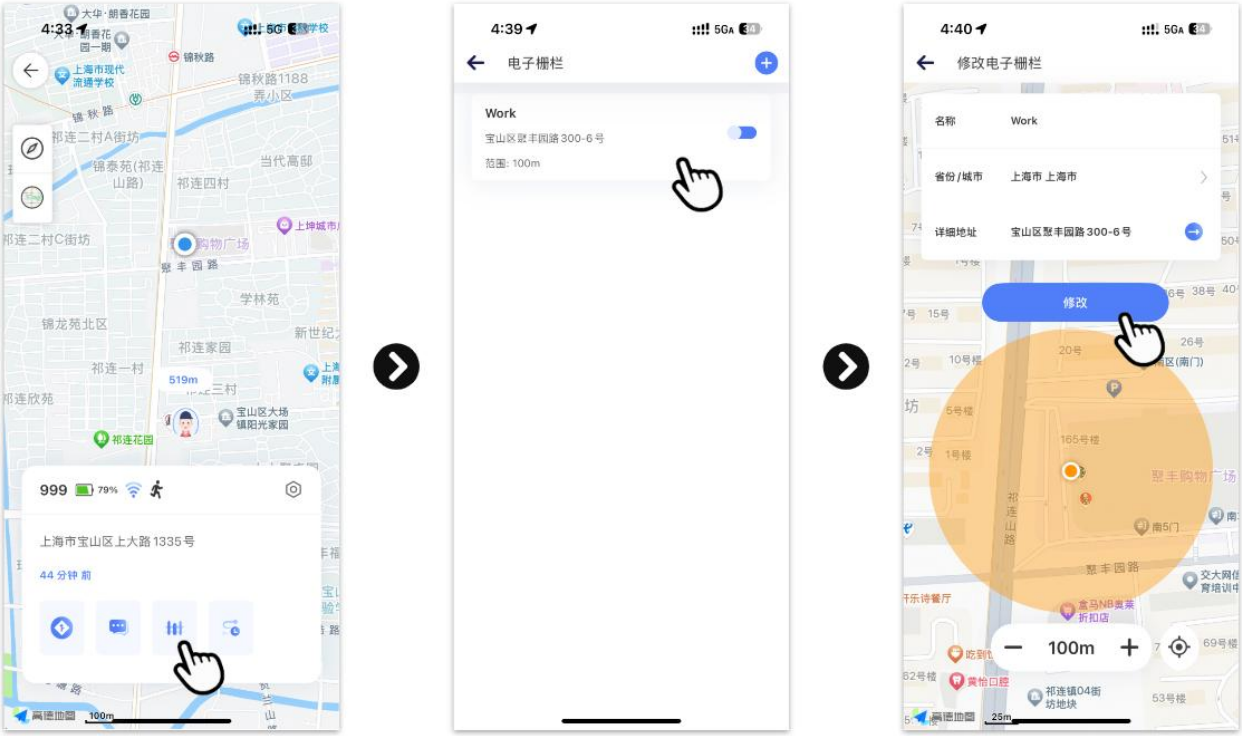

# 8.历史轨迹

(1) 用户在查找设备页，点击 进入历史轨迹页

(2) 点击 < 或 > 切换年或月

(3) 选择相应日期后，点击确认，等待系统绘制轨迹行程

(4) 用户可以点击 重新选择其他日期与时间

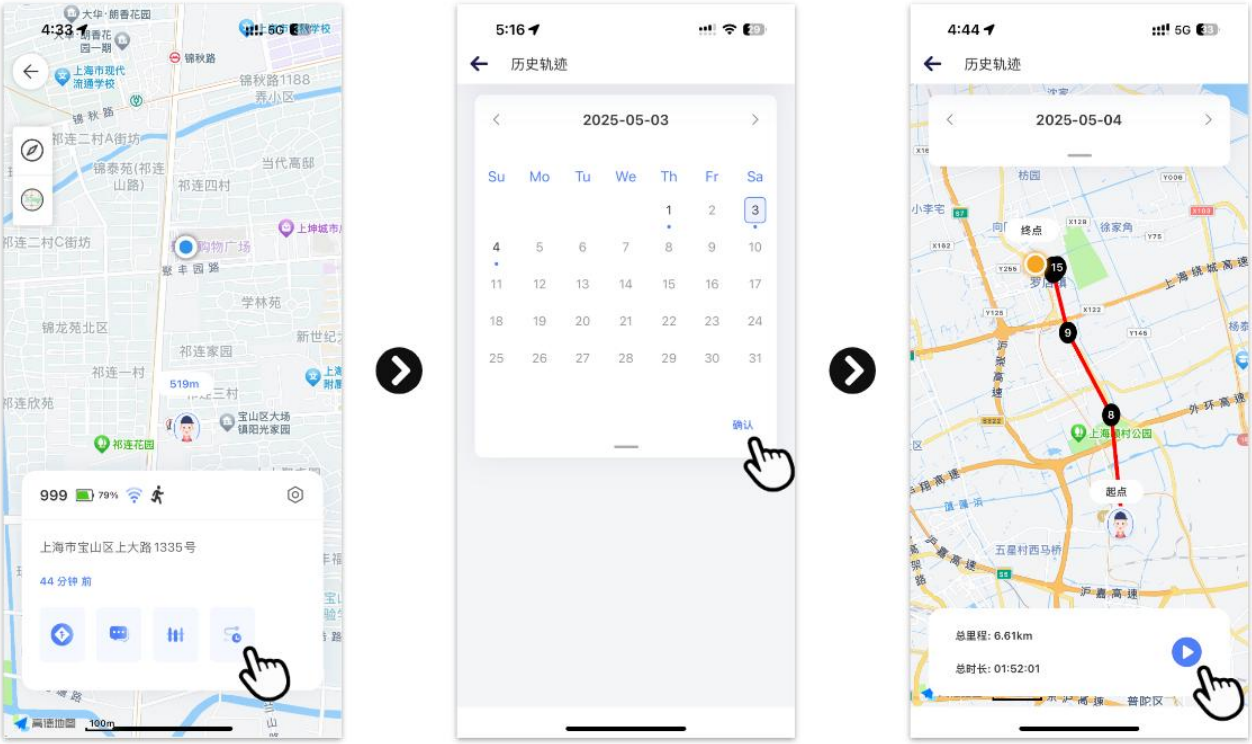


]

# 9.设备详情

## 9.1. 设备基本信息

(1) 用户在设备地图页，点击 进入设备详情页

(2) 可以查看设备拥有人，IMEI 序列号，SIM 卡号码等

(3) 用户可以选择【解绑】此设备

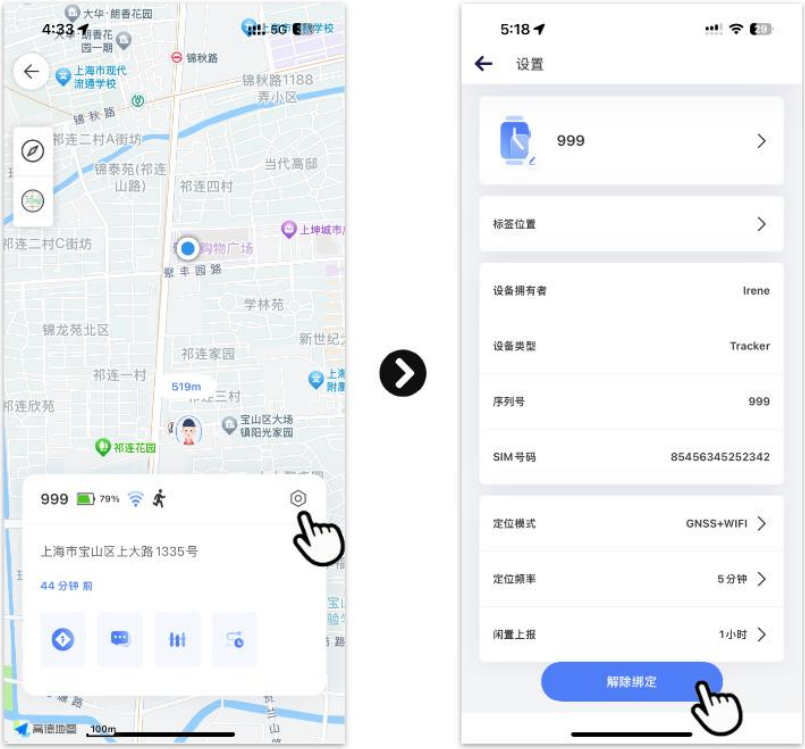

## 9.2. 修改定位频率

(1) 用户可以调整设备定位频率(快~慢)来增加使用时长

(2) 点击【定位频率】，出现选项窗

(3) 点击【确定】，系统将出现 “指令已发送” 弹窗通知

(4) 等待下次设备更新状态

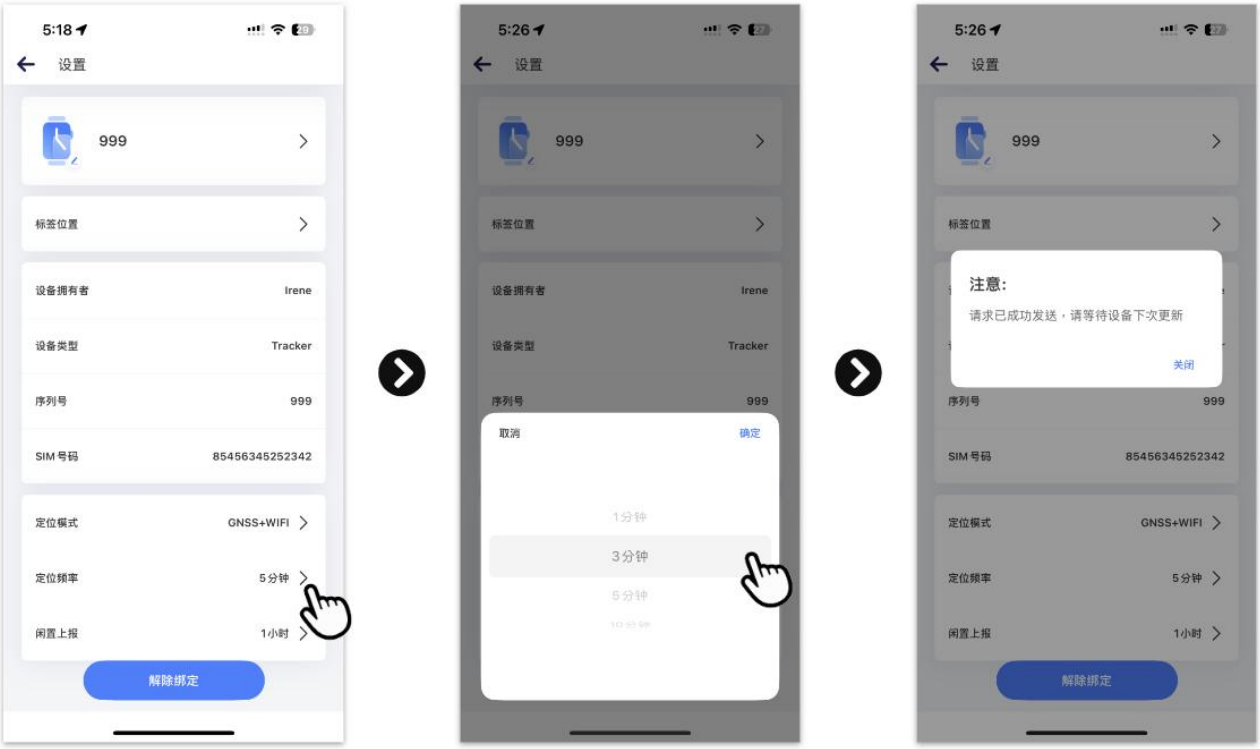

## 9.3. 修改定位模式

(1) 用户可以调整定位模式(GNSS、WIFI、GNSS+WIFI、停用)来节省电耗

(2) 用户点击【定位模式】，出现选项窗

(3) 点击【确定】，系统将出现 “指令已发送” 弹窗通知

(4) 等待下次设备更新状态

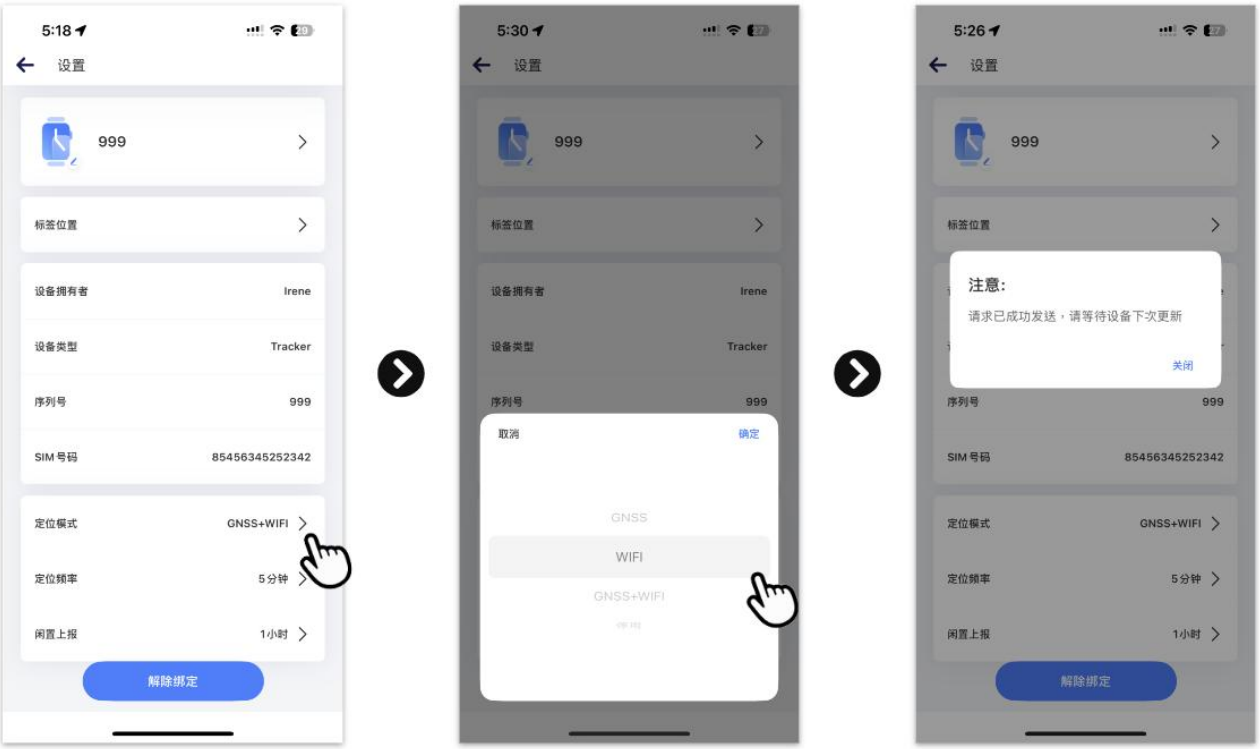

## 9.4. 修改上报频率

(1) 用户可以调整设备休眠时的上报频率(快~慢)来控制响应时间

(2) 点击【闲置上报】，出现选项窗

(3) 点击【确定】，系统将出现 “指令已发送” 弹窗通知

(4) 等待下次设备更新状态

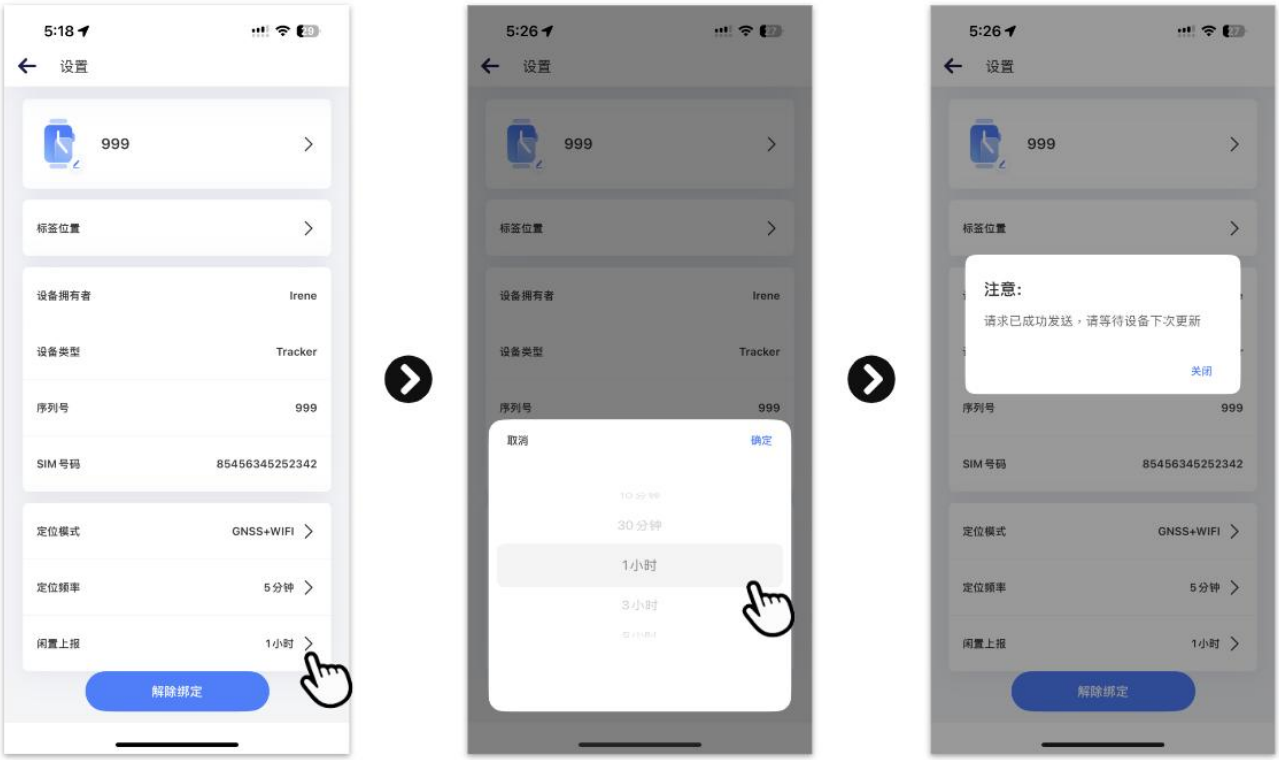

# 10. 个人中心

## 10.1. 我的二维码

(1) 点击【我的二维码】，跳转用户二维码信息页

(2) 当其他用户使用【扫一扫】扫描此二维码，系统将发起好友邀请确认弹窗

(3) 是，则向此好友发出邀请并等待结果；否，则关闭弹窗

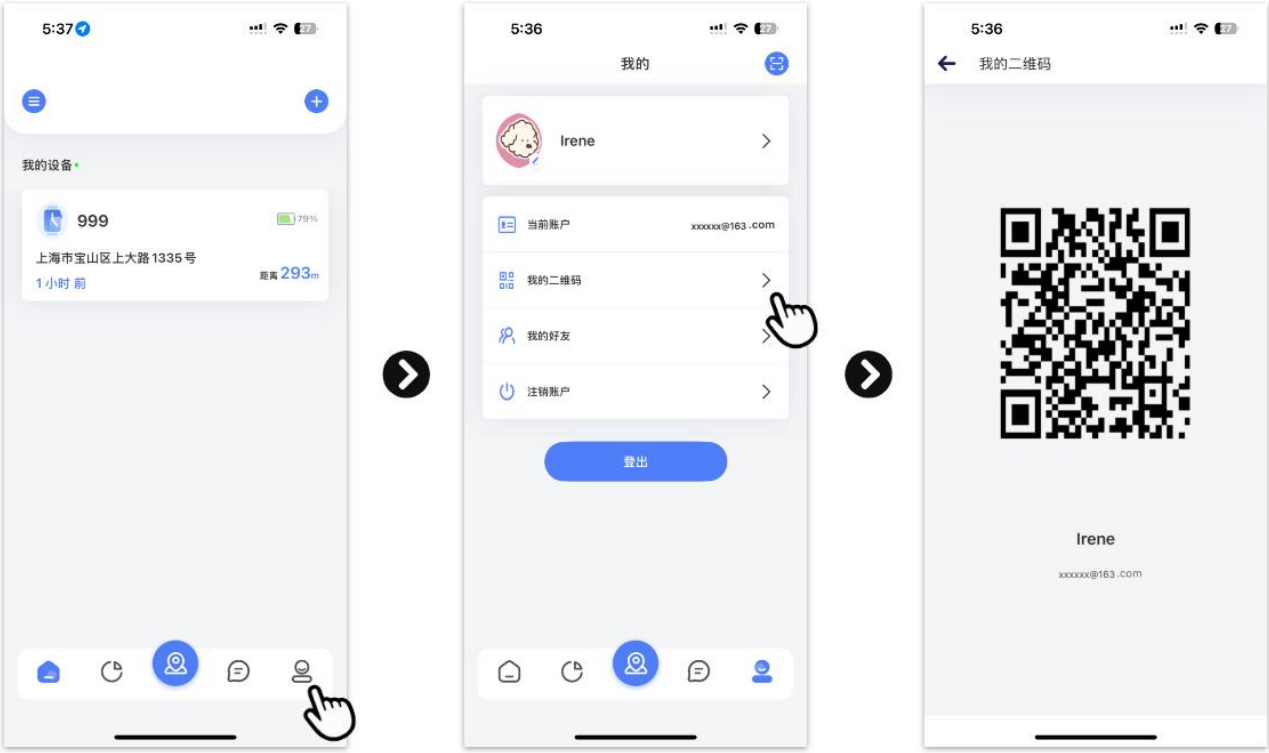

# 10.2. 我的好友

## 10.2.1. 好友列表

(1) 用户可以查看所有已通过的好友信息

(2) 用户可以左滑删除好友

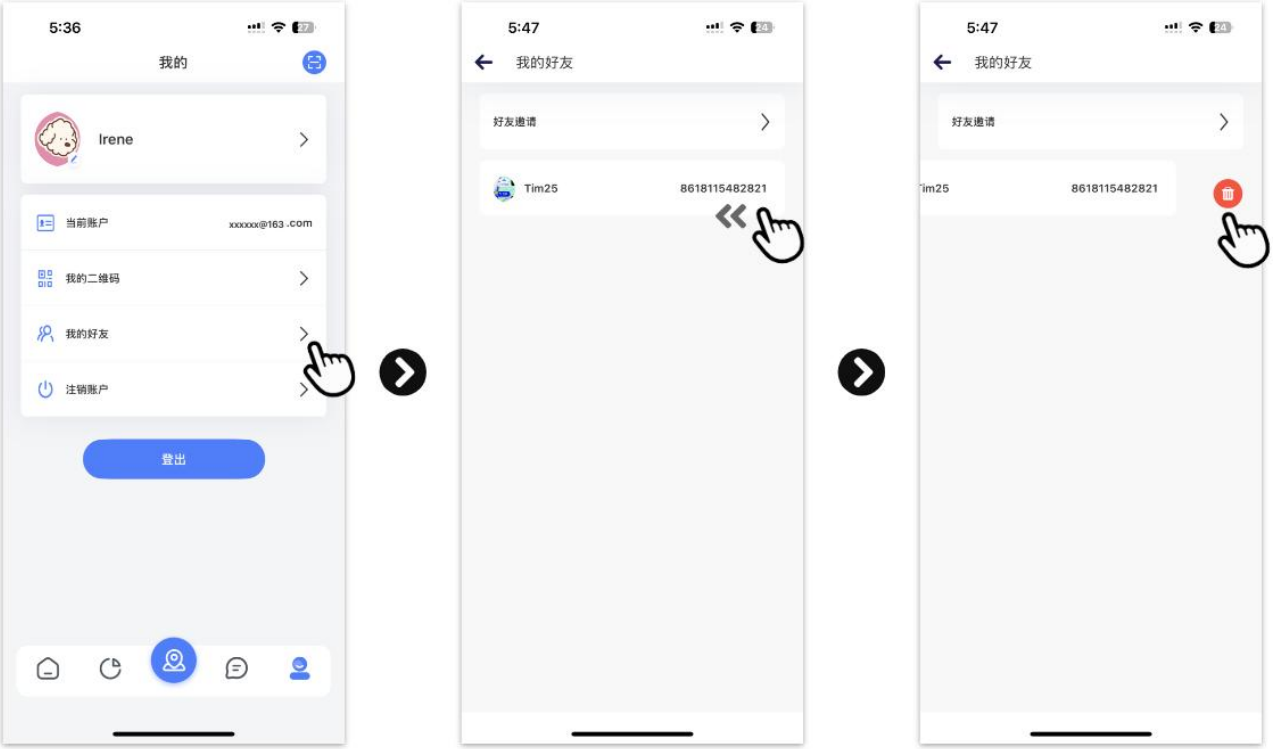

## 10.2.2. 好友邀请列表

(1) 点击【好友邀请】，跳转好友邀请列表页

(2) 出现所有发起邀请的好友列表

(3) 同意，则通过此次邀请；拒绝，则取消此次邀请

(4) 如双方为好友，则可以相互绑定设备并共享设备位置

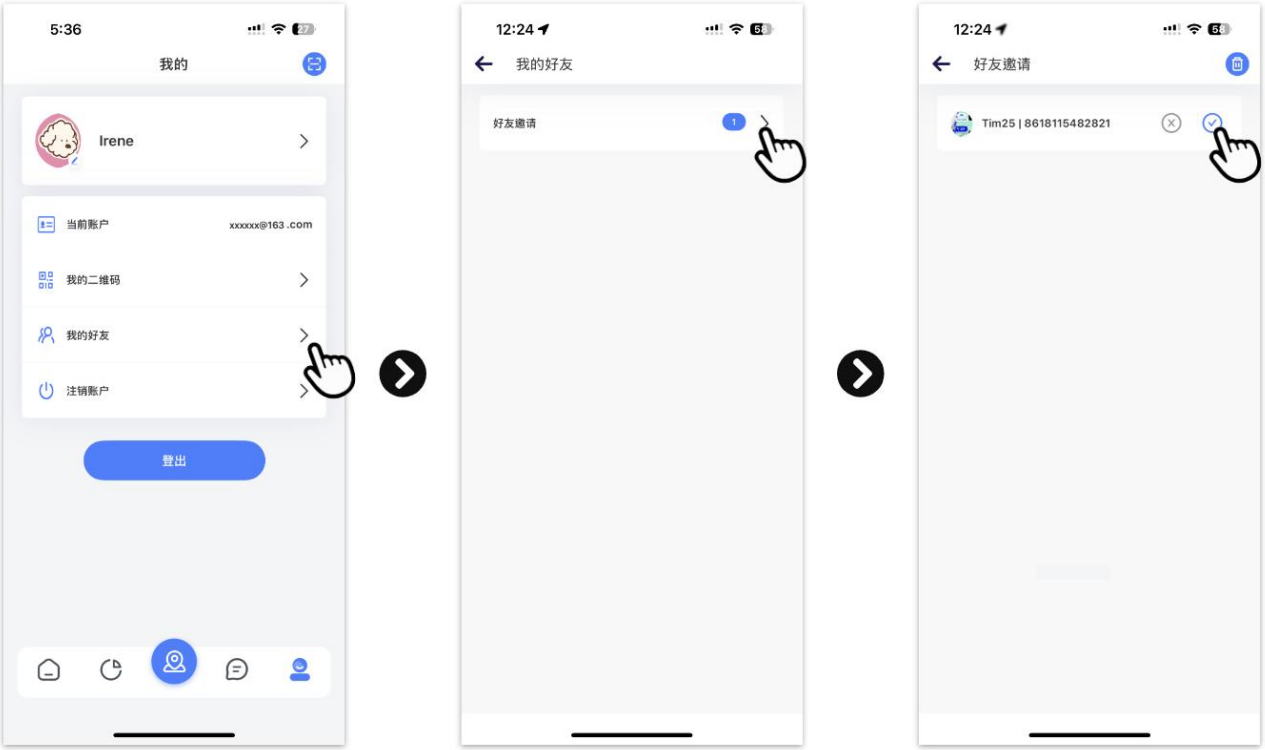

# 10.3. 注销账号

(1) 点击【注销账户】，出现二次确认弹窗

(2) 点击【确认】，等待后台清除该账户信息

(3) 完成清除，用户退回至登录页

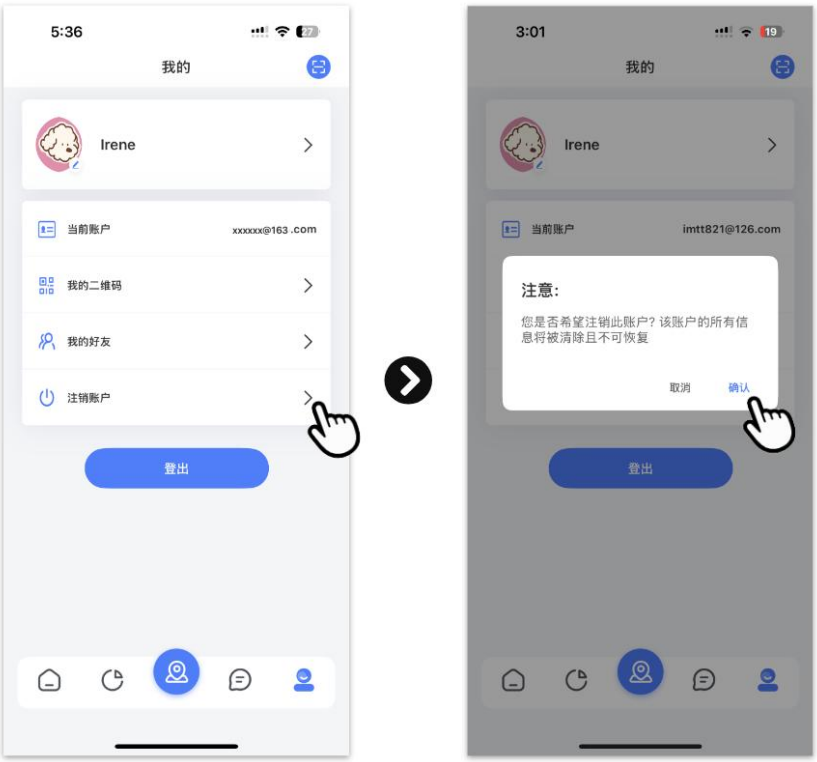

# 11. 修订文档

## 11.1. 修订纪录

| 版本 | 修订日期 | 修订内容 |
|---|---|---|
| V1.0 | 2025/1/19 | 创建文档 |
| V1.1 | 2025/4/11 | 更新文档 |
| V1.2 | 2025/5/7 | 更新文档 |
| V1.3 | 2025/6/8 | 更新文档 |